Wat is nieuw in ZCBS (v4.03)

ZCBS versie 4.03 (release 28 januari 2017)

Aanpassingen/uitbreidingen van eerdere/latere ZCBS-versies:

- Versie 4.07 (release voorjaar 2019)
- Versie 4.06 (release 20 augustus 2018)
- Versie 4.05 (release 27 januari 2018)
- Versie 4.04 (release 4 augustus 2017)
- Versie 4.03 (release 28 januari 2017)
- Versie 4.02 (release 16 augustus 2016)

Aangepast/bijgekomen t.o.v. de vorige distributieversie 4.02 van 16 augustus onder meer:

a. **Uitbreiding/aanpassing zoekmogelijkheden** (*Homepage*)
nieuw per 28-12-2016
De config parameter voor de item 'Zoeken in' op de homepage:
`$VELDMENU = "opsomming veldnummers";`
is uitgebreid met de mogelijkheid

- de default waarde aan te passen (door het betreffende veld als eerste in het uittrekmenu te plaatsen);
- het voorheen vaste item 'Alle velden' weg te laten of naar een andere locatie in het uittrekmenu te verschuiven;
- het voorheen vaste item 'objectnummer/databasenummer' weg te laten of naar een andere locatie in het uittrekmenu te verschuiven.

Weglaten van 'Alle velden' of 'objectnummer/databasenummer' gaat door het plaatsen van een minteken voor het veldnummer, resp. dus -02 en -00.

b. **Uitgebreide sorteermogelijkheid zoekresultaat** (*Homepage*)
nieuw per 29-12-2016
Voorheen kon via de config parameter:
`$SORTEREN = 1;`
een zeer beperkte (default) sorteermogelijkheid worden opgegeven.

Door eventueel het opgeven van 4 veldmogelijkheden kon slechts gesorteerd worden op de velden: titel (05), vervaardiger (07), datering (08) of adres (14).
In de nieuwe ZCBS-versie kan nu:

1. Op **alle** velden worden gesorteerd;
2. Op een koppel (van twee) velden worden gesorteerd;
3. De volgorde van keuzes op de homepage volledig bepaald worden;
4. De oude keuzemogelijkheid van sorteren op recordnummer (02) en ongesorteerd (00), worden verwijderd.

In nevenstaand voorbeeeld (bidprentjes Heemkundekring Weerderheem) kan gekozen worden op:

- Sortering op veld achternaam (veld: 05) en tegelijkertijd voornaam (veld: 07);
- Sortering op geboortedatum (veld: 08);
- Sortering op datum overlijden (veld: 22).

met als bijbehorende config parameter:
`$SORTEREN = "0507 08 22 -00 -02";`
Sorteermogelijkheid voor interne pagina's kan de systeembeheer laten afwijken van de globale instelling door het extra definieren van de config parameter:
`$SORTEREN_INT = "...";`

---

c. **Selectie maken uit een zoekresultaat** (*Zoekresultenpagina*)
nieuw per 26-09-2016
Een selectie kan worden gemaakt uit de gevonden records in een (of meerdere) zoekresultaten.
Dat kan bijvoorbeeld worden gebruikt bij de organisatie van een expositie, zoeken naar illustraties voor een

publicatie, samenstellen van een ZCBS-slideshow en het maken van bulkaanpassingen.
Deze mogelijkheid kan worden aangezet door het opgeven van de SPECiale systeemzoekopdracht:

```
SPEC6
```

Daarna verschijnt bij elk object binnen een zoekresultaat een 'checkbox'.
Onderaan de zoekresultatenpagina kan men de aangevinkte records opslaan onder een bepaalde naam.
Indien deze naam al eerder is gebruikt bij een selectie, worden de aangevinkte records *toegevoegd* aan de eerder geselecteerde gegevens.
Deze gegevens worden op de webserver opgeslagen in de map:

```
public_html/[beeldbank_naam]/downloads/
```

Alle eerder opgeslagen selecties worden getoond op de webpagina *'Zoekgeschiedenis'* van de gegevensbeheerder.
Daar kunnen de selecties getoond, gekopieerd, dan wel verwijderd worden.
Bovengenoemde instelling is uit te schakelen met systeemzoekopdracht:

`SPEC0` of alleen: `SPEC`

Het is de bedoeling in de toekomst meer tijdelijke instelmogelijkheden te maken via de `SPECx` (met x = getal) zoekopdracht. `DEBUG1`, `DEBUG2`, `DEBUG3` vallen in feite hier ook onder.

LET op:
Bij het opgeven van de sysysteemzoekopdracht SPEC (en ook bij DEBUG) mag direct daarna (gescheiden met spatie) ook eventueel nog een zoekopdracht worden opgegeven! Bijvoorbeeld:

```
SPEC6 aardewerk
```

d. **Aanpassing onderschrift bij gallery weergave** (*Zoekresultenpagina*)
nieuw per 09-09-2016
Onder de afbeelding bij de gallery weergave van een zoekresultaat kon een onderschrift geplaatst worden door in de config file de volgende opdracht te geven:

```
$GALLERY_CAPTION = 1;
```

Onder de afbeelding verscheen dan:

```
Recordnummer: inhoud_titelveld
```

De opdracht is als volgt uitgebreid:

```
$GALLERY_CAPTION = veldnummer;
```

Onder de thumbnail verschijnt dan de inhoud van het betreffende veld.
Zie de advertentiebeeldbank van Stichting Oud Zoeterwoude (gallery weergave):
http://beeldbank.oudzoeterwoude.nl/cgi-bin/advertenties.pl?veld=all&display=gallery
waar de subrubriek (veld 3) wordt getoond onder de thumbnail.

---

e. **Pop-up disclaimer bij onbekende vervaardiger/auteur/fotograaf** (*Objectpagina*)
nieuw per 21-10-2016
Indien in veld 07 (vervaardiger, maker, auteur, fotograaf), het woord *Onbekend* is vermeld, wordt er automatisch door ZCBS een disclaimer bij geplaatst met een standaard (algemene) tekst.
Daarbij wordt uitgegaan dat men eerst de nodige actie heeft ondernomen om de betreffende maker van het object te vinden (tot 70 jaar na de dood van de maker kan auteursrechten rusten op het betreffende object).
De gegevens/systeembeheerder wordt ten zeerste aangeraden altijd iets te plaatsen in het betreffende veld en dus een leeg veld te vermijden!
De default tekst is eventueel te veranderen via de config file:

```
$ONBEKEND= <<EOR;
Blabla blabla bla bla blabla bla bla.
Blabla blabla bla.
Blabla blabla bla bla bla.
EOR
```

Wanneer wordt opgegeven:

```
$ONBEKEND = " ";
```

(een spatie als inhoud) wordt geen tekst getoond.
Deze optie geldt voorlopig alleen bij foto-beeldbanken

f. **Plaatsing meerdere afbeeldingen binnen een objectpagina** (*Objectpagina*)
nieuw per 30-08-2016
Wanneer men meerdere (nagenoeg gelijke) afbeeldingen heeft die bij hetzelfde object/record horen, kan men deze plaatsen in een zgn. carrousel.
De aanvullende afbeeldingen worden opgesomd in een *(intern)* ZCBS-veld aangegeven in de config file via:

```
$VELD_CARROUSEL = veldnummer;
```

Vanzelfsprekend moet men daarnaast ook het veld een naam geven, bijvoorbeeld:

```
$fieldname{"VELD17"} = "Aanvullende images"; ## (bij gekozen veld17)
```

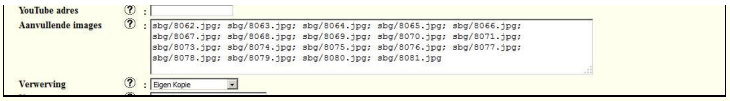

In het betreffende (formulier)veld plaatst men vervolgens alle aanvullende afbeeldingen.
Deze afbeeldingen moeten in de map `/large` en eventueel in de map `/100pct` worden geplaatst of in een submap in deze map. Men kan bijvoorbeeld een submap `/large/carrousel` maken of bestandsnamen kiezen als `00123-01.jpg`, `00123-02.jpg`, etc.

- Zie het voorbeeld (objecten-beeldbank) op:
  www.zcbs.nl/cgi-bin/objecten.pl?ident=105
- Zie het voorbeeld (foto-beeldbank) op:
  www.zcbs.nl/cgi-bin/beeldbank.pl?ident=150
  Zie nevenstaande afbeelding.
- Zie het voorbeeld (boeken-beeldbank) op:
  www.zcbs.nl/cgi-bin/library.pl?ident=010

Nadeel bij deze afbeeldingsmethode is wel, dat alle afbeeldingen moeten worden geladen voordat de pagina zelf kan worden getoond (*let dus op de grootte van de bestanden*).
Daarentegen worden wel de afbeeldingen dan direct getoond bij het aanklikken daar deze in de cache van de browser blijven zitten.
Ook kan van elke carrousel-afbeelding een 100% weergave worden getoond.

g. **Zoom mogelijkheid bij Google Maps afbeelding** (*Objectpagina*)
nieuw per 20-09-2016

Voorheen werd een statisch Google Map afbeelding getoond indien in de config file was opgenomen:

```
$GOOGLE_MAP = "veldnaam of veldnummer";
$fieldname{"veldnaam/veldnummer"} = "Google Maps;
```

In de nieuwe (dynamische Google Maps) versie is:

1. de afbeelding te vergroten of te verkleinen;
2. direct de 'Streetview optie' op te roepen;
3. direct te switchen tussen kaart en satelliet afbeelding;
4. door te klikken op de Google logo in de 'full screen mode' te openen.

Een Google Map wordt getoond indien:

- in het betreffende veld de GPS-coördinaten worden opgegeven, *of*
- indien plaats en straatnaam/huisnummer van de afbeelding bekend is.

Voor deze nieuwe Google Map wordt men verzocht om een (gratis aan te vragen) *Google key* op te geven in de config file, bijvoorbeeld:

```
$GOOGLE_KEY = AIzaSyDL0M9ELxL64Q1rrfl9iIpv0abcdefghij;
```

h. **Tonen streetview afbeelding naast die van de standaard Google Maps** (*Objectpagina*)
nieuw per 21-09-2016

Indien zowel de GPS-coördinaten zijn opgegeven alsook minimaal de kijkrichting (en eventueel de vericale kijkhoek en zoomfactor), wordt naast de Google kaart/satelliet afbeelding, ook een streetview afbeelding van de betreffende locatie getoond.
Deze afbeelding is (zoals standaard bij een streetviewafbeelding):

1. in te zoomen
2. de locatie aan te passen
3. door te klikken op de Google logo in de 'full screen mode' te openen.

Voorbeelden zijn te vinden op de demo foto-beeldbank website:
www.zcbs.nl/cgi-bin/beeldbank.pl

---

i. **Dynamisch aanpassen streetview afbeelding incl. locatie/orientatie binnen ZCBS** (*Formulierpagina*)
nieuw per 13-10-2016

Zowel de (GPS)-positie, de kijkrichting en de zoom van de streetview-afbeelding is dynamisch *op de formulierpagina* aan te passen. De betreffende streetview waarden worden direct getoond onder de streetview afbeelding.
Beide afbeeldingen zijn met elkaar gekoppeld: een aanpassing in de ene afbeelding wordt meteen geëffectueerd in de andere.
De getoonde aangepaste waarden kunnen gekopieerd worden naar het betreffende Google maps ZCBS-veld.
Na opslaan hiervan in de ZCBS-database, wordt de aangepast kijklocatie en kijkrichting op de objectpagina getoond.
De streetview waarden zien er bijvoorbeeld als volgt uit:

```
(52.8017319811323, 4.757754297785027), 147.94495007333, 4.5369650560461, 2.159509048046329
```

welke resp. aangeeft: GPS-kijklocatie, kijkrichting (t.o.v. noorden), verticale kijkhoek (horizontaal = 0 graden) en de zoomfactor.
Zie bijvoorbeeld: www.zcbs.nl/cgi-bin/beeldbank2.pl?ident=00012&upd_form=edt

j. **Tijdelijk plaatsen streetview afbeelding onder de object afbeelding** (*Formulierpagina*)
nieuw per 14-10-2016

Om de GPS-kijklocatie, kijkrichting, verticale kijkhoek en zoomfactor van een afbeelding te bepalen m.b.v. een aangezette streetview afbeelding, kan deze afbeelding (die standaard bij het veld 'Google maps' wordt getoond, direct onder de afbeelding van het betreffende record worden geplaatst.
Deze mogelijkheid kan *tijdelijk* worden aangezet door

het opgeven van de SPECiale systeemzoekopdracht:
`SPEC7`
Deze optie werkt alleen op de formulierpagina.
De instelling is weer uit te schakelen met systeemzoekopdracht:
`SPEC0` of alleen: `SPEC`
De streetview-afbeelding wordt *niet getoond* bij het betreffende ZCBS-veld als deze is geplaatst onder de record afbeelding.



k. **Dynamisch zoeken van GPS-coördinaten bij een Google kaart/satelliet map** (*Formulierpagina*)
nieuw per 20-10-2016
Wanneer voor een locatie geen streetview afbeelding aanwezig is (bijvoorbeeld bij bepaalde kleine wegen, in bossen, weide en strand), kan *door het verplaatsen van de rode marker* op de kaart/satellietafbeelding op de formulierpagina, eenvoudig de betreffende GPS-coördinaten verkregen worden.
De GPS-coördinaten verschijnen tijdens het verplaatsen van de rode marker onderaan de afbeelding.
Deze coördinaten kunnen vervolgens geplaatst worden in het betreffende ZCBS-veld.

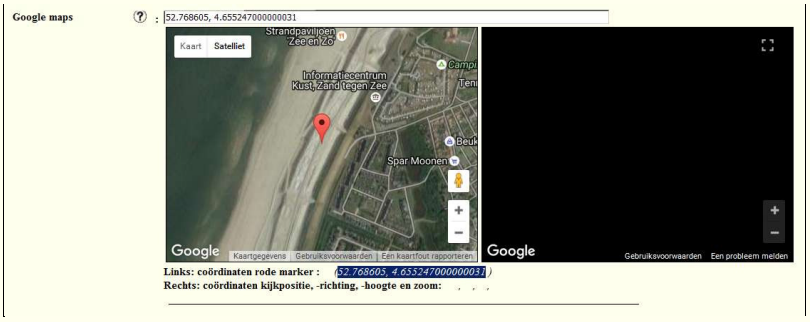

l. **Verwijderen record behalve de afbeelding** (*Formulierpagina*)
nieuw per 14-11-2016
Bij het verwijderen (del) van een record wordt standaard:
1. de database record (de metadata) verwijderd;
2. de bestandsnaam van de afbeelding herbenoemd (met underscore en datum)

Wanneer de SPECiale systeem(zoek)opdracht `SPEC8` is gegeven, wordt bij het gebruik van de del(ete) knop *alleen* het database record (de metadata) verwijderd.
Op de getoonde pop-up verschijnt de tekst:
`Object == .... == wordt definitief verwijderd!`
`======> (m.u.v. de 'large' image) <======`
`== Ok? ==`

Deze SPECiale omgeving blijft van kracht tot het wordt uitgeschakeld middels systeemzoekwoord:
`SPEC0` of alleen: `SPEC`

---

m. **Toegangsrechten aanvulling** (*Systeem*)
nieuw per 18-12-2016
Interne bezoekers met permissie 1 (gegevensbeheerders), 2 of 3, kunnen uitgesloten worden om afbeeldingen tot 100pct te vergroten (dan wel PDF's te tonen bij OCR-documenten).
Dat kan nu gerealiseerd worden door de betreffende persoon permissie 1-, 2- of 3- te geven.
Deze uitbreiding geldt voor alle type beeldbanken.

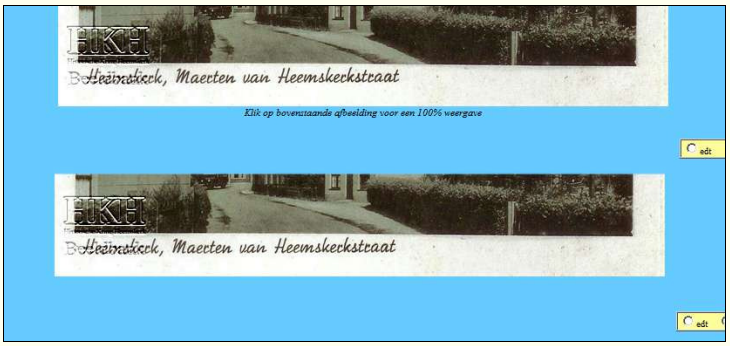

n. **Sterke verbetering ZCBS-performance** (*Systeem*)
nieuw per 04-11-2016
Door delen van de ZCBS-code slimmer te gebruiken (en soms te herschrijven), kon de verwerkingstijd bij (vooral) het zoeken aanzienlijk worden verbeterd.
Zo bedraagt in de huidige versie het zoeken in een beeldbank met 81.098 foto's ca. 12.2 seconden in het ongunstigste geval. In de nieuwe versie is dat verlaagd naar 4.4 seconden. Ook in databases met 'slechts' enkele duizenden records is verbetering van de snelheid duidelijk merkbaar.

In een (voorlopige) testomgeving met 183.000 bidprentjes (Heemkundekring Weerderheem/Valkenswaard) ging in het ongunstige geval van het zoeken, de verwerkingstijd van 25.5 seconden (!) naar 9.9 seconden.
Performance van ZCBS blijft een aandachtspunt en zal waarschijnlijk in de toekomst nog tot verdere verbeteringen leiden.

o. **Zandloper bij langere verwerkingstijd** (*Systeem*)
nieuw per 13-11-2016
Bij het zoeken in meer dan 60.000 databaserecords kan de verwerkingstijd duidelijk boven de 1.0 seconde



komen te liggen. Voor de website bezoeker/ster is het in dat geval onduidelijk of er al dan niet wat gebeurt.
Via de config file kan er in dat geval dan een animatie van een roterende tekst worden aangezet:

```
$PLEASE_WAIT = 10;
```

waarbij het getal (in dit voorbeeld 10) het aantal seconden aangeeft van een volledige rotatie.
Door een getal te kiezen waarbij de langste zoekopdracht (leeg veld) net geen volledige rotatie geeft, heeft de gebruiker een indicatie hoelang maximaal eventueel gewacht moet worden.
Bij databases met minder dan ca. 30.000 records heeft deze parameter in principe vanzelfsprekend geen zin.

`$PLEASE_WAIT` kan ook parameters bevatten om de zandloper wat aan te passen.
Deze parameters zijn gescheiden door een spatie en geven respectievelijk aan:

- Tijd volledige omwenteling in seconden
- Achtergrondskleur volledige ring
- Kleur ringfragment
- Grootte ring
- Getoonde tekst

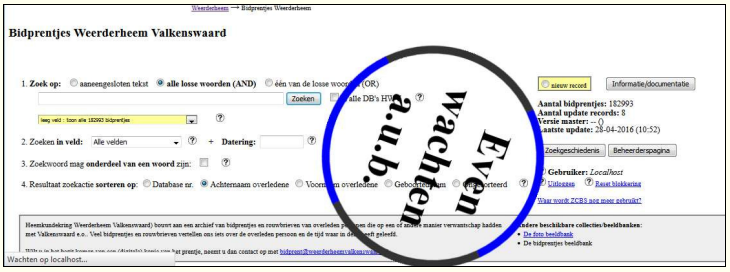

Bijvoorbeeld:

```
$PLEASE_WAIT = '15 #333333 blue 400px <span style="font-size:80px;font-weight:bold;
position:relative;top:50px;">Even wachten<br>a.u.b.<span>';
```

Wordt parameters op het eind van het commando niet opgegeven, dan geldt de default.

p. **Versturen emails vanuit ZCBS via interne Perl-module** (*Systeem*)
nieuw per 28-11-2016
E-mails verstuurd bij onder meer aanpassing databaserecords door gegevensbeheerders of reactie websitebezoekers gaan standaard niet meer via de sendmail utility van de hostprovider doch nu via de Perl module `sendmail.pm` welke bij de instellingen is geplaatst in de webserver map `/cgi-bin/misc/`.
De reden hiervoor is dat instellingen van de mailserver bij hostproviders kunnen afwijken afwijken van wat algemeen gebruikt wordt. Daarnaast kunnen de e-mail mogelijkheden, indien noodzakelijk, eventueel t.z.t. ook worden uitgebreid (smtp- naast localhost-verzending).

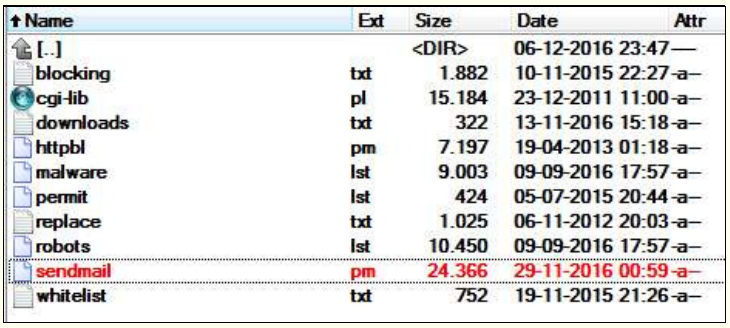

Name	Ext	Size	Date	Attr
[..]		<DIR>	06-12-2016 23:47	—
blocking	txt	1.882	10-11-2015 22:27	a–
cgi-lib	pl	15.184	23-12-2011 11:00	a–
downloads	txt	322	13-11-2016 15:18	a–
httpbl	pm	7.197	19-04-2013 01:18	a–
malware	lst	9.003	09-09-2016 17:57	a–
permit	lst	424	05-07-2015 20:44	a–
replace	txt	1.025	06-11-2012 20:03	a–
robots	lst	10.450	09-09-2016 17:57	a–
sendmail	pm	24.366	29-11-2016 00:59	a–
whitelist	txt	752	19-11-2015 21:26	a–

---

q. **En verder**

- Veld nr. 17 toegevoegd aan ZPBS type beeldbanken.
- Via een extra parameter in de hyperlink kan een slideshow zonder navigatie gestart worden: `&search_dt=5-600-1`
- Informatietekst bij invulformulier bijlagen: "Aanpassen van deze bijlage maakt eventuele 'tegelijkertijd aangebrachte' andere wijzigingen in metadata ongedaan! Verwerk aanpassingen metadata separaat.".
- Extra parameter bij de Google coordinaten ten behoeve van *locaal* afwijkende map-type en map-layout: `[r|s|h|t]` voor locaal: [roadmap|satellite|hybrid|terrain] en `[a|b|c]` voor locaal [enkel map|enkel streetview|beide].
  Zo kan een Google map op een individueel record afwijken van de globale instelling.

- Diverse interne code aanpassingen onder meer ter verbetering performance en leesbaarheid.
- Diverse kleine aanpassingen.
- Diverse bugs gefixed (met dank aan de melders!).